ACTUALIZACIONES

09/03/2025 Actualización (ver 3.1.2)

1. **Gráfico MAPA.** Listado de calles, exportar a archivo .PDF y .DOCX

Se visualizan sin portal: , o vía: por delante. Se ordenan correctamente. Agregada línea Subtotal por calles

23/02/2025 Actualización (ver 3.0.1)

2. **Gráfico HORAS.** Nuevo diseño definiendo Noche, Mañana y Tarde

3. **Nuevo Campo calculado. (**suma los valores que se encuentren en el campo seleccionado)

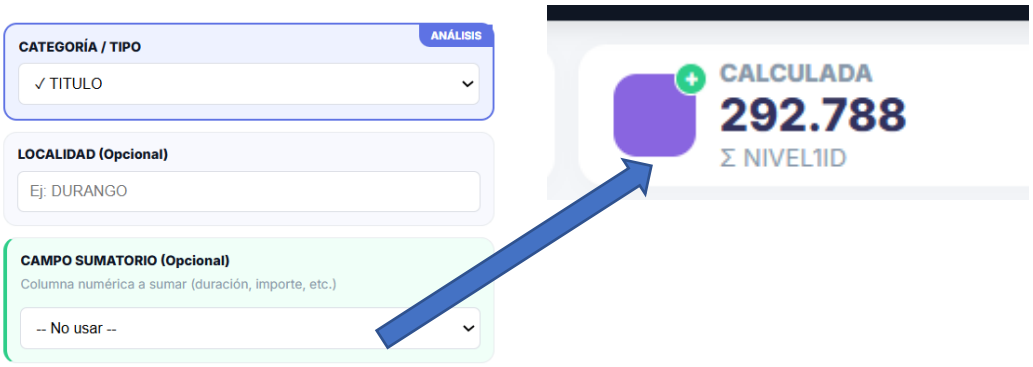

ACTUALIZACIONES

18/02/2025 Actualización (ver 3.0) “CLIMA”

1. **Gráfico EVOLUCION TEMPORAL. Añadida nueva opción “Clima” sólo en “Diario”**

ACTUALIZACIONES

2. Síntesis. Análisis mejorado

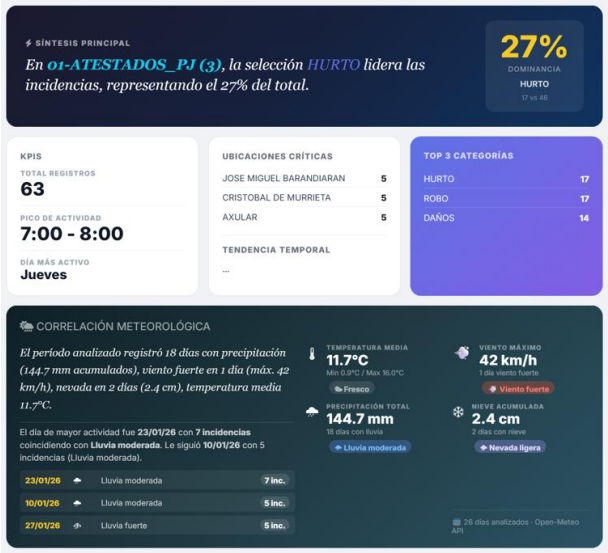

3. Gráfico Temporal, diferenciación de Fines de Semana por colores (incluido viernes)

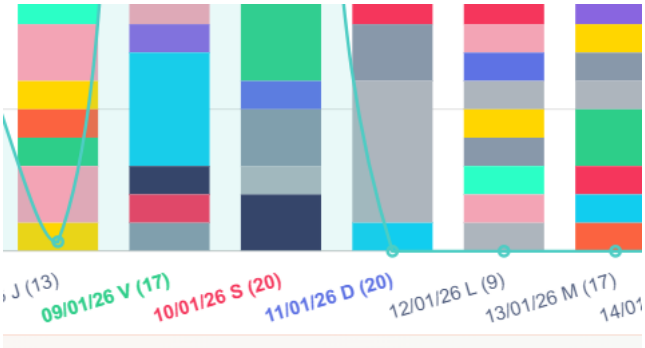

18/02/2025 Actualización (ver 2.0.6)

4. Gráfico EVOLUCION TEMPORAL. Añadida nueva opción “Diario”

ACTUALIZACIONES

18/02/2025 Actualización (ver 2.0.5)

Filtros Extra. ”CONFIGURACIÓN DE COLUMNAS”. Anteriormente sólo se podía hacer un único filtro que es CATEGORIA, con este cambio se puede combinar con 2 filtros más. Realizando agrupaciones por los 3 filtros incluyendo CATEGORIA.

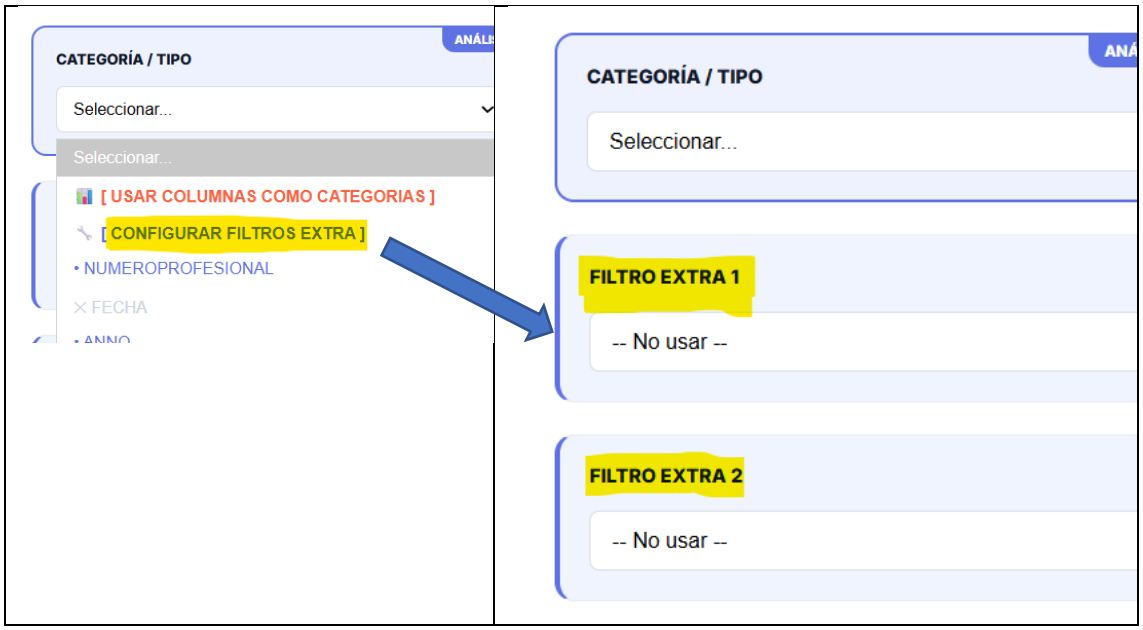

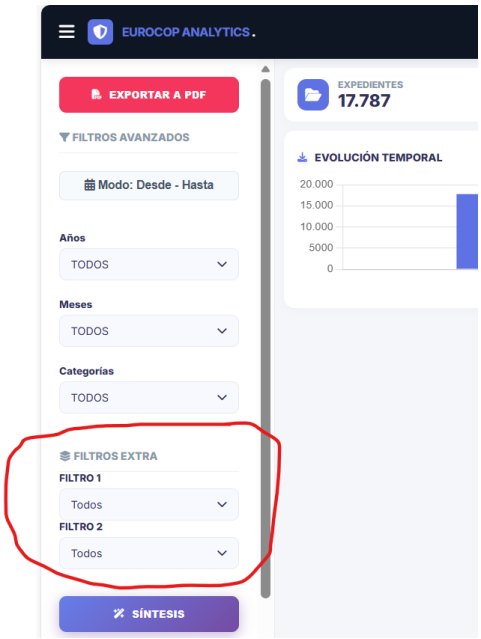

2. **Ajustes visuales en el menú configuración.**

3. **Pantalla adaptativa a móviles pegables (Samsung Fold 6)**

ACTUALIZACIONES

15/02/2025 Actualización (ver 2.0.4)

1. **Gráfico Evolución Temporal. Añadido botón "Ver relato de datos"**

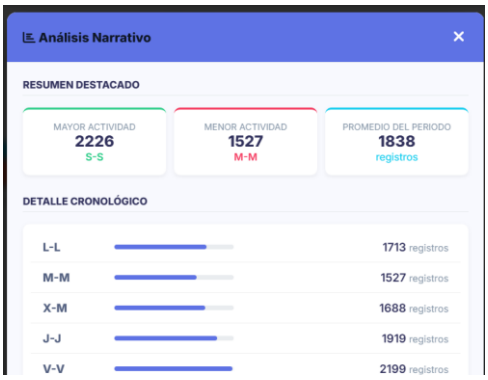

15/02/2025 Actualización (ver 2.0.3)

1- **Gráfico Mapa.** Establecer colores de puntos por diferentes años
2- **Reajusta gráfico Horas.** No se ajustaba
3- **Eliminar botón "PREVISIÓN TACTICA".** Es parecida a síntesis.. hay que darle otra vuelta
4- **Archivos grandes + de 1mg.** Opción de seleccionar los últimos 4 años o todos para poder filtrar datos a traer y mejorar la velocidad

ACTUALIZACIONES

04/02/2025 Actualización (ver 2.0.2)

1. **Menu Categorias/Busqueda.** Cambiados los textos de botones por iconos. Ajuste correcto de los tres botones. El botón limpiar filtro, elimina el contenido del texto y vuelve a seleccionar todas las categorías. (anteriormente solo borraba el texto)

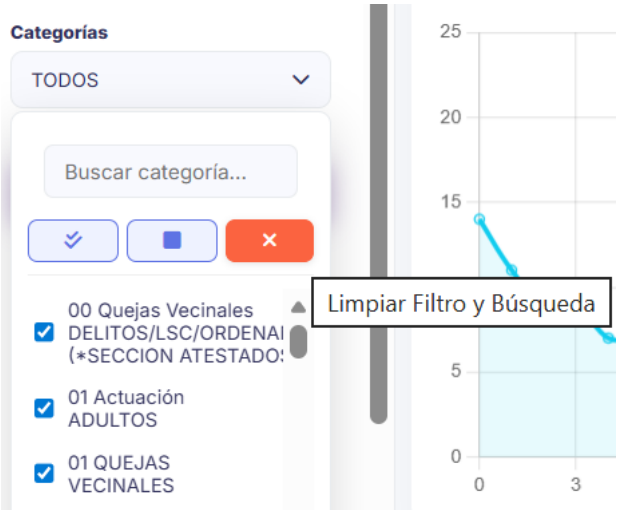

2. **Fecha desde-Hasta. incorporar** flecha para agilizar la selección de días concretos copia la fecha desde y la pega en fecha hasta.

3. **Informes SINTESIS** (estado actual) **PREVISION TACTICA (**operativa a realizar en relación a histórico de datos)

ACTUALIZACIONES

01/02/2025 Actualización (ver 2.0.1) * Refactorización completa de código*

4. **Mapa (Búsqueda de zonas).**

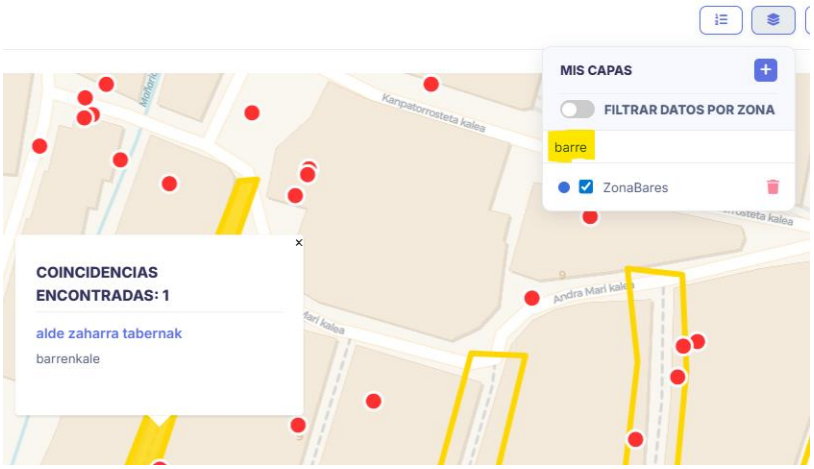

5. **Ajustes en la generación de archivos PDF**

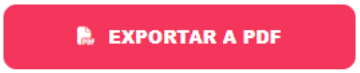

6. **Bug arreglado.** Cuando todos los graficos estaban en formato de datos, al cambiar el grafico mapa a formato de datos cambiaba el resto a modo grafico automáticamente. Arreglado

01/02/2025 Actualización (ver 2.0.0) * Refactorización completa de código*

7. **Nueva opción VIDEOTUTORIALES.**

8. **Zona Critica (recorre las tres zonas con mas incidencias)**

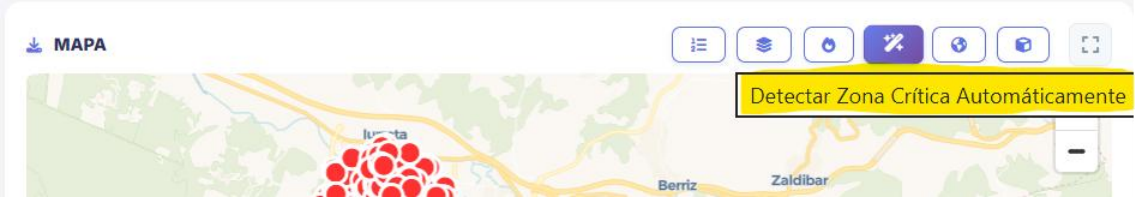

ACTUALIZACIONES

30/01/2025 Actualización (ver 1.6.9)

1. **Nueva opción FILTRO. Añadido filtro entre Fechas, por dias**

2. **Numero Catalogo Hechos**. En diferentes configuraciones delante del catalogo de hechos si hay números, cuando se presentan en la informe síntesis suprime ese número ya que crea confusión ya que sale ese número.

3. En caso de no existir HORA en el Excel , **no se visualizará el grafico HORAS**

29/01/2025 Actualización (ver 1.6.8)

Corregidos BUGs

1. Filtro de meses no cambiaba los idiomas
2. Al cargar archivo "**UnificacionTotal.xls**", al seleccionar "usar columnas como categorias", no funcionaba.
3. 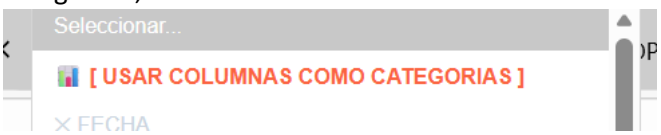

ACTUALIZACIONES

29/01/2025 Actualización (ver 1.6.7)

CONFIGURACION cuando se carga el Excel solo pide los datos de CATEGORIA y LOCALIDAD, ya que por defecto carga el resto de campos del Excel en los campos de configuración y por defecto los oculto ya que no se suelen modificar.

Si quisiéramos visualizar el resto de campos pinchar "Mostrar campos configurados"

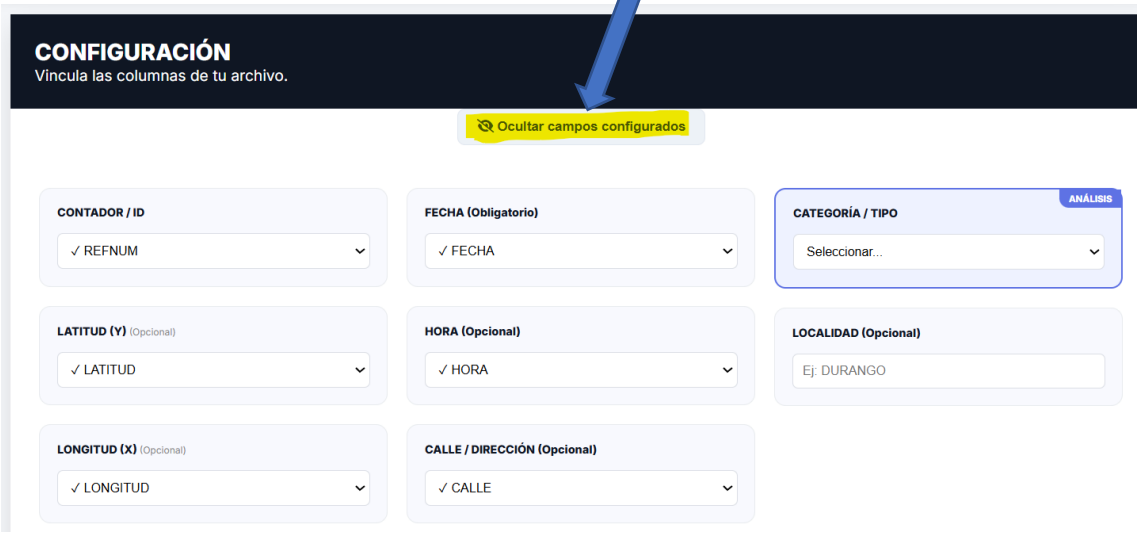

ACTUALIZACIONES

2. Gráfico temporal. Al pasar por el gráfico que solo se visualice el dato de el tipo de categoría seleccionado (antes visualizaba todos, lo cual quedaba muy farragoso)



3. Mapa. Corrección a la hora de mayor concentración de puntos, zona más caliente.

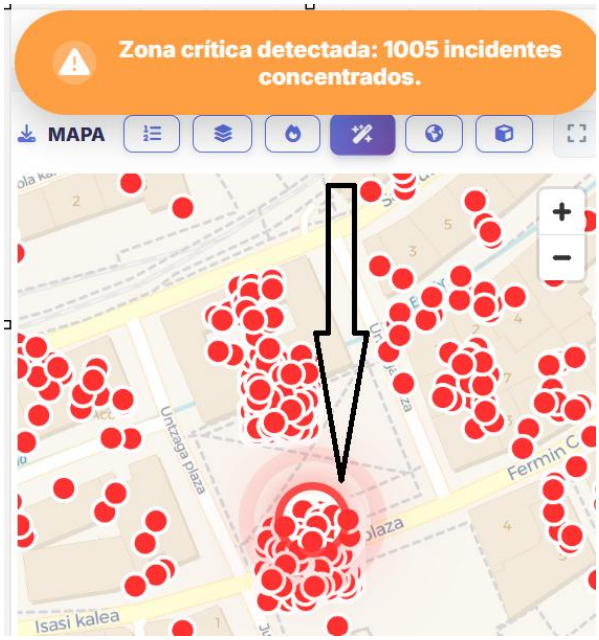

4. Sintesis. Añadido el nombre del archivo, para mejorar el informe aclaratorio

ACTUALIZACIONES

28/01/2025 Actualización

1. **Mapa (zonas)** agregar **nombre** y **descripción** a la zona donde se construye las zonas. https://geojson.io/

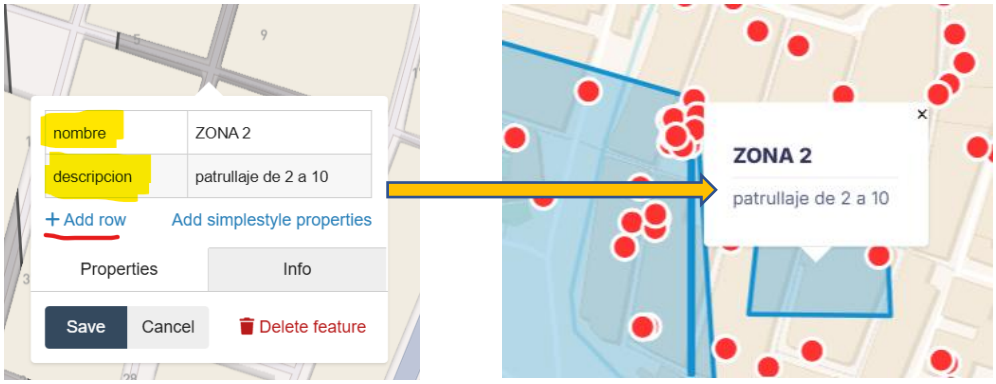

2. **Mapa. Zona Critica . Nuevo botón para indicar la zona centro más conflictiva**

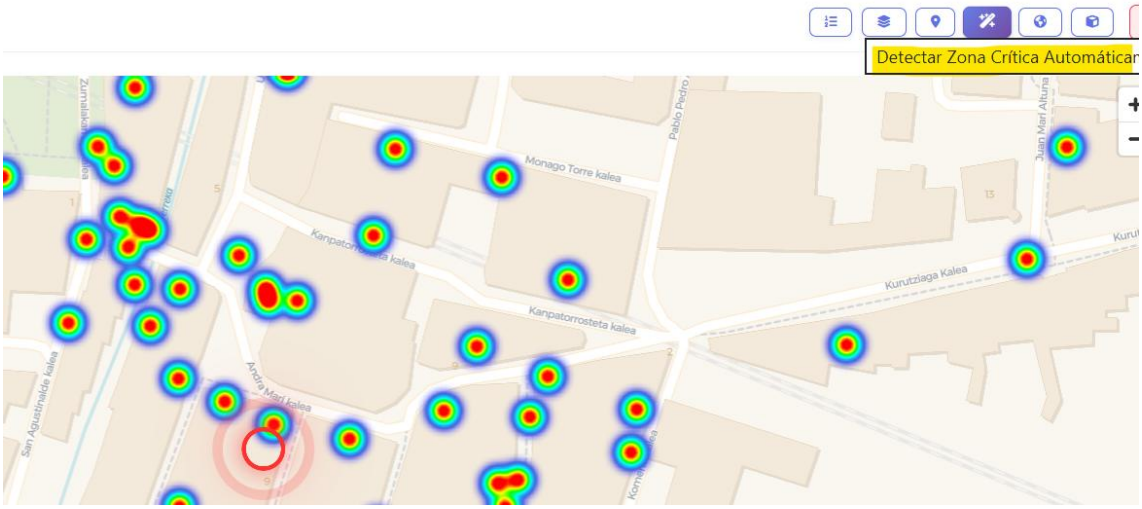

ACTUALIZACIONES

27/01/2025 Actualización

1. **Opción descargar gráficos como imágenes**

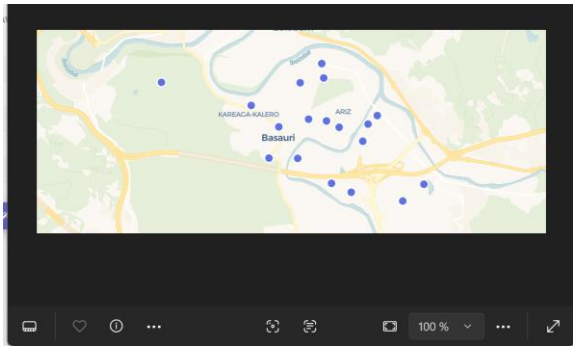

2. **Grafico Evolución Temporal,** al hacer click sobre el grafico que aparezcan los expedientes que son

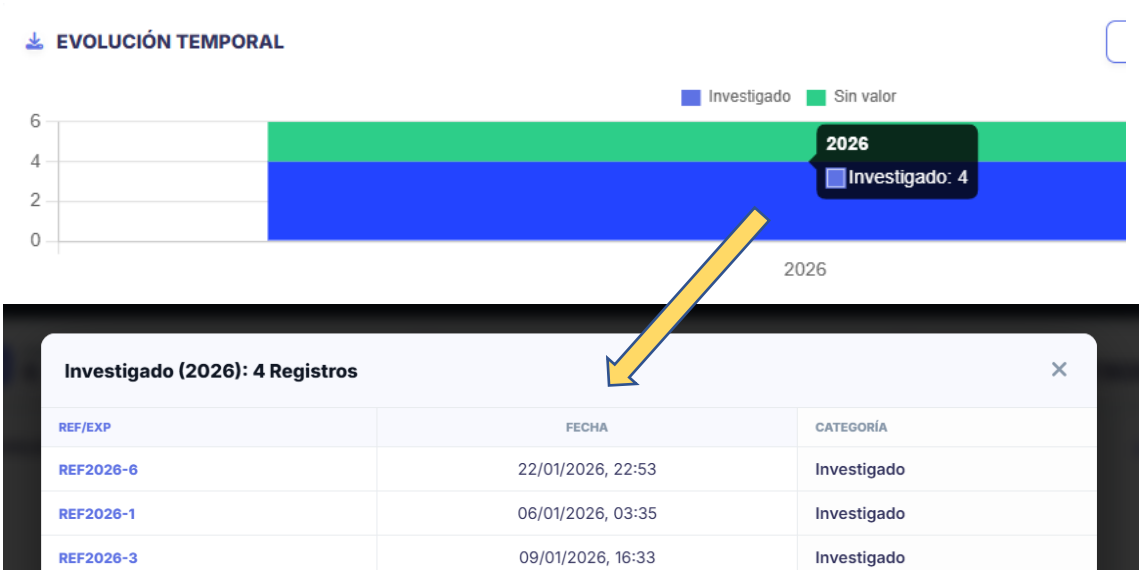

3. **Grafico Mapa,** al hacer click sobre una calle que se posicione sobre el mapa (tener en cuenta que si no existe esa calle en Google maps, no se ubicará. Esta opción sólo sale si tenemos vías en los datos de eurocop.

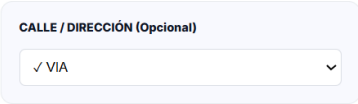

ACTUALIZACIONES

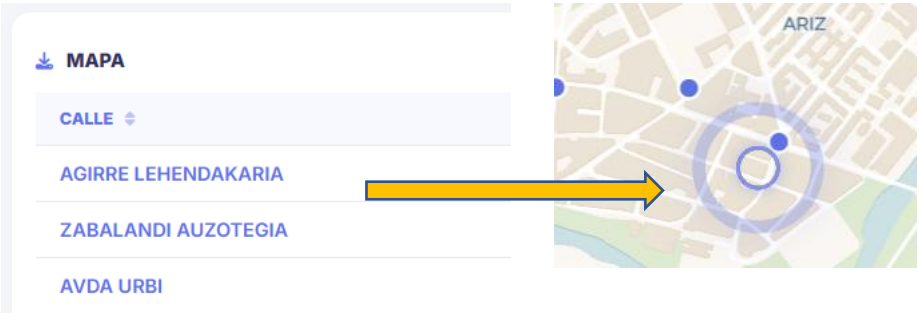

4. **Informe SINTESIS**. En caso de haber campo VIAS/CALLES, agrega ese dato al informe

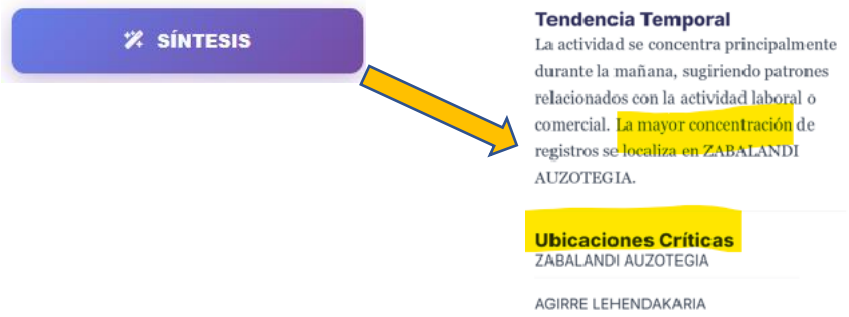

5. **Gráfico MAPA.** Agregada direcciones en caso de que exista el campo.

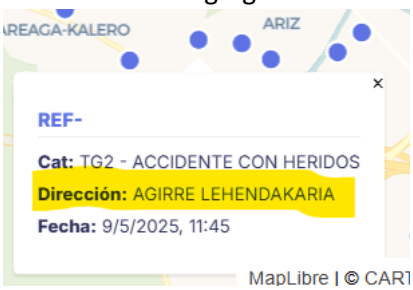

ACTUALIZACIONES

6. **Grafico TEMPORAL.** Resumen de barra por categoría con clasificación de mayor a menor, para una mejor aclaración de datos.

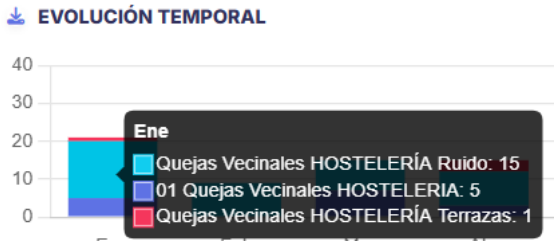

25/01/2025 Actualización

1. **Mapa** (agrupación de puntos), cuando las coordenadas coincidían en un mismo punto sólo se visualizaba un punto, ahora agrupa puntos alrededor.

2. **Configuración**. Añadido agregación de campo calles

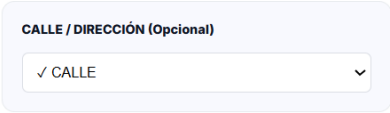

3. **Gráfico Mapa** (agregado menú calles), en caso de tener calles visualiza las calles

25/01/2025 Actualización

1. **Síntesis** (nueva función) Sobre los datos filtrados realiza un análisis resumen

ACTUALIZACIONES

2. **Traducción de Síntesis** a Diferentes idiomas

22/01/2025 Actualización

1. Mapa, agregado la posibilidad de agregar capas (zonas policiales) archivos .geojson. **"Filtrar datos por zona"** Solo analiza los puntos que estén dentro de las zonas policiales

   Si desactivo el filtro, vuelve toda los puntos

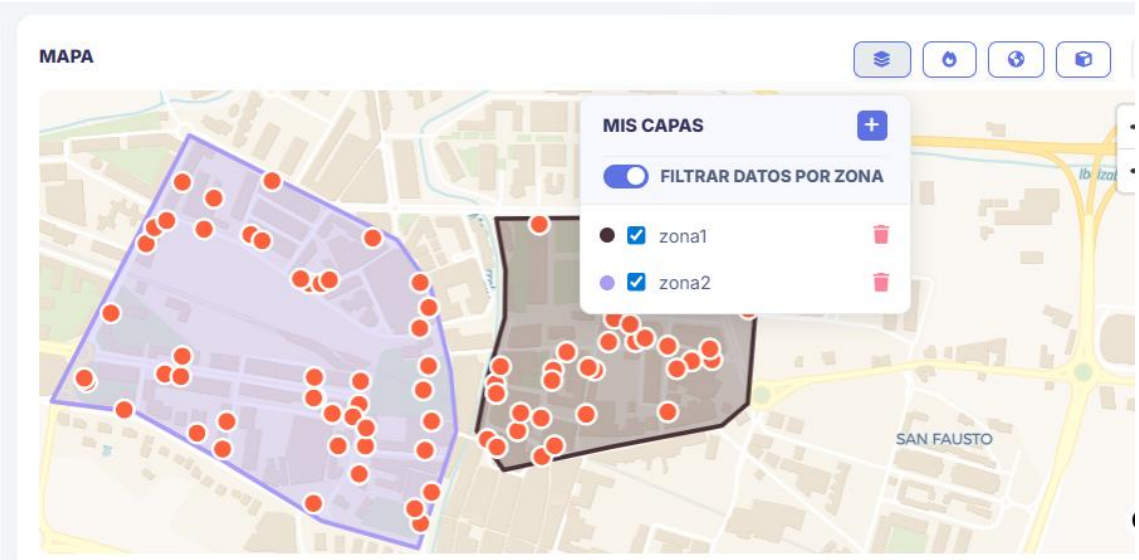

21/01/2025 Actualización

2. Agregado campo de busqueda en categorias

ACTUALIZACIONES

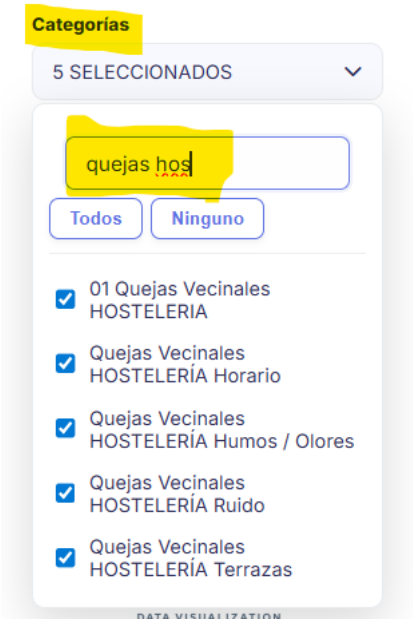

19/01/2025 Actualización

3. Posibilidad de descarga de memorias base, para que se puedan importar en diferentes entornos. (primero se descargan y luego desde eurocop se importan)

4. Adaptación a pantallas móviles, ya que no terminaba de ajustarse a dichas pantallas

18/01/2025 Actualización

5. Cuando se cambian años, tipo gráfico de gran tamaño, que visualice mensaje

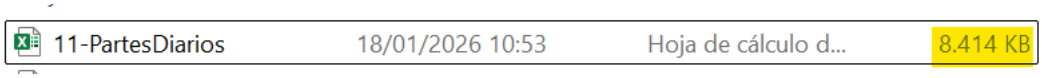

ACTUALIZACIONES



6. Cuando se abren archivos grandes, >4mg te avisa porque va haber ralentización al ser muchos datos, y te informa que es conveniente realizar filtros por años en las consultas de Eurocop (Memorias)

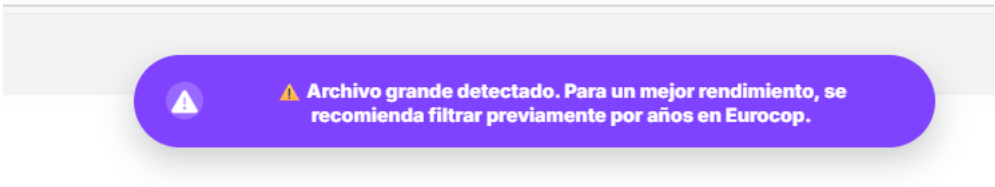

7. Control de versiones genero archivo “version.js” para entorno programación
8. Retoques adaptativos a diferentes pantallas

17/01/2025 Actualización

9. Grafico colores por categorías

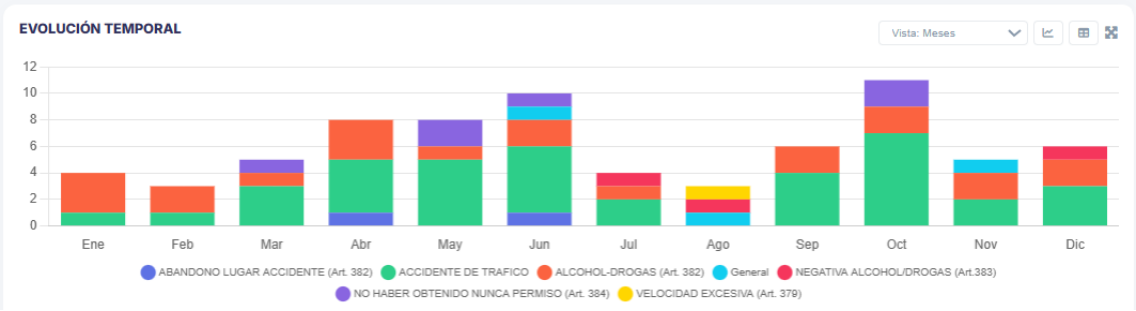

10. **Grafico de líneas**

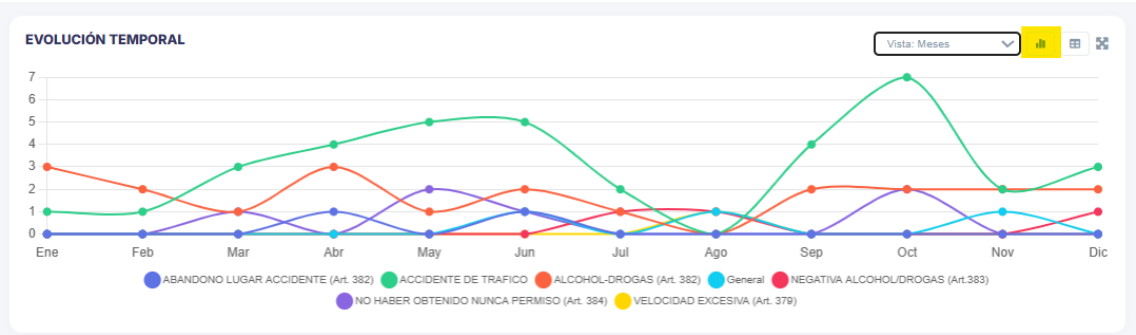

11. **Si no hay coordenadas latitud, longitud NO se visualiza GRAFICO de MAPA**

15/01/2025 Actualización

12. Ordenar listado descendentemente

ACTUALIZACIONES

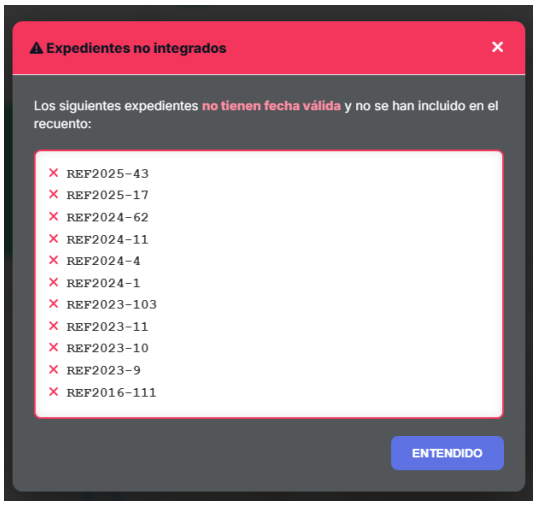

14/01/2025 Actualización

1. Tomar campo REFNUM predeterminadamente, a veces cogía otra campo.

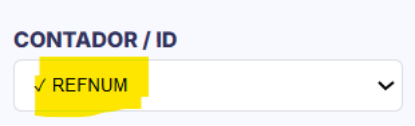

2. Gráfico “Top Tipos” cuando tenía textos largos no ajustaba bien

13/01/2025 Actualización

1. Titulo del Archivo Excel quitado del encabezamiento, ahora aparece dentro del Dashboard



2. Corrección de problema con fechas, ya que aplicaba el formato ingles y descuadraba los datos

3. Sustituir el campo _EMPTY por BLANCO (campo sin valor)

ACTUALIZACIONES

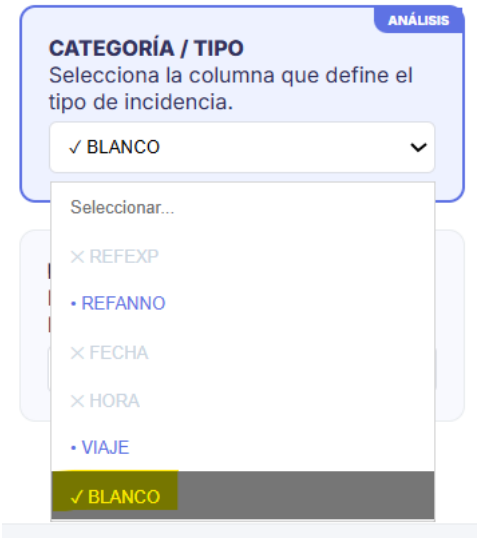

4. Visualiza los registros que NO se cargan en la estadística porque carece de Fecha

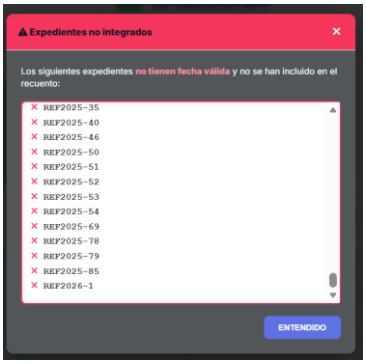

12/01/2025 Actualización

1. Incorporación de idiomas CASTELLANO, EUSKERA, CATALAN, GALLEGO

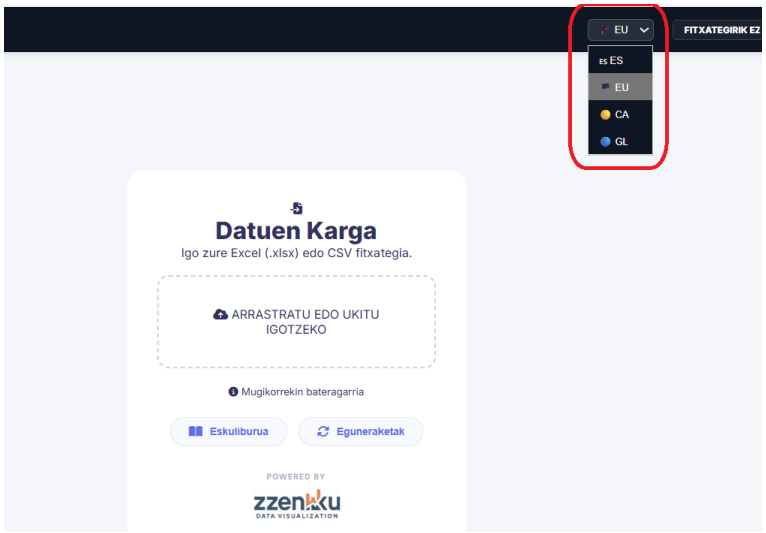

ACTUALIZACIONES

2. Mejora del Grafico TOP TIPOS Auto adaptable cuando se maximiza el gráfico

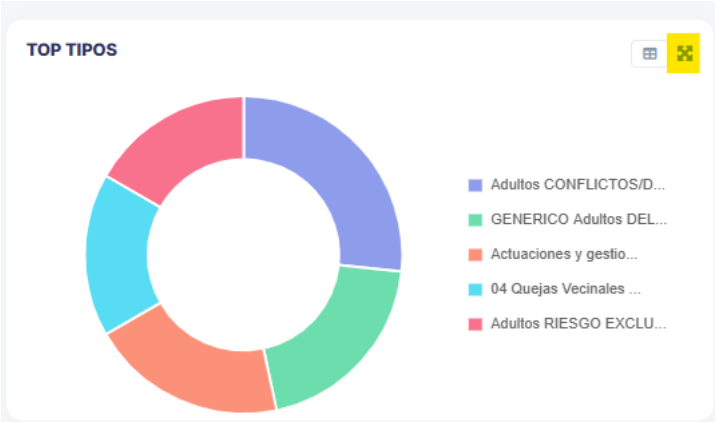

3.Opción de visualización de gráficos sin campos LATITUD ni LONGITUD

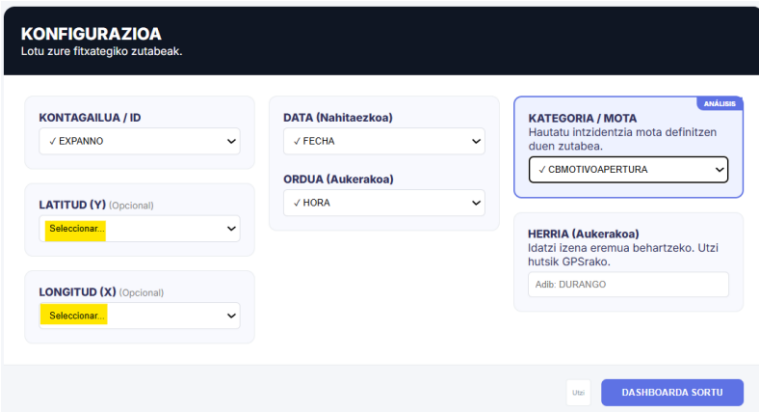

11/01/2025 Actualización

1. Añadida opción Grafico Temporal “vista Trimestral”

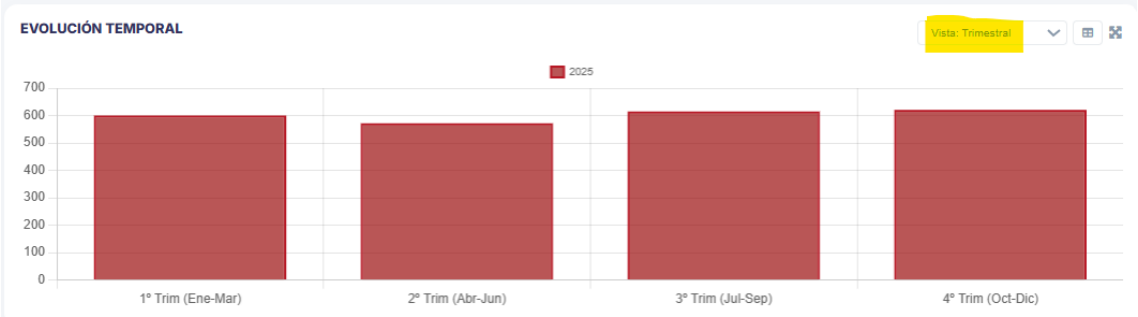

2. Solucionado el problema de que no se visualizaban el total de registros, ya que se eliminaban las filas que no tenían latitud y longitud, ahora se visualizan todos los registros

ACTUALIZACIONES

3. Visualización de datos en los Gráficos

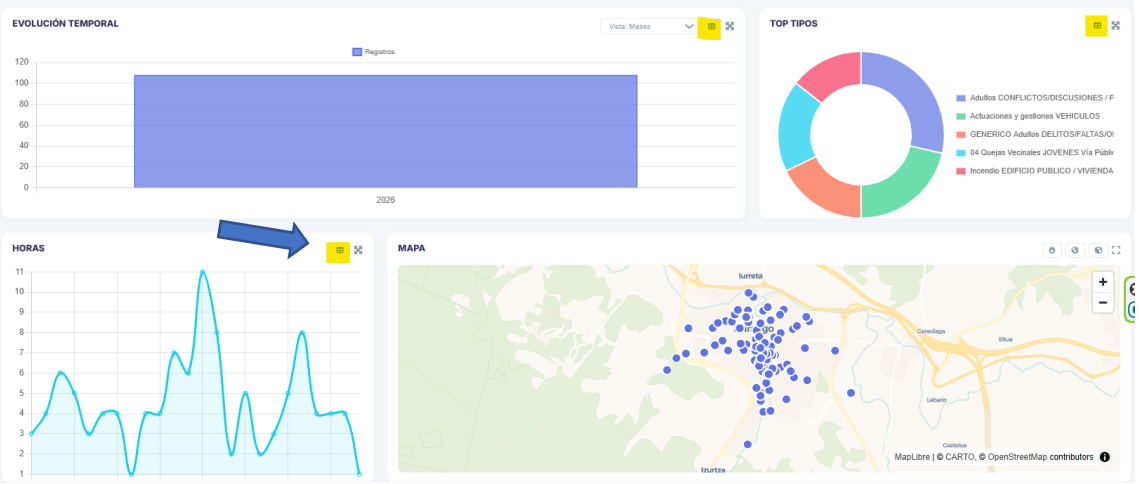
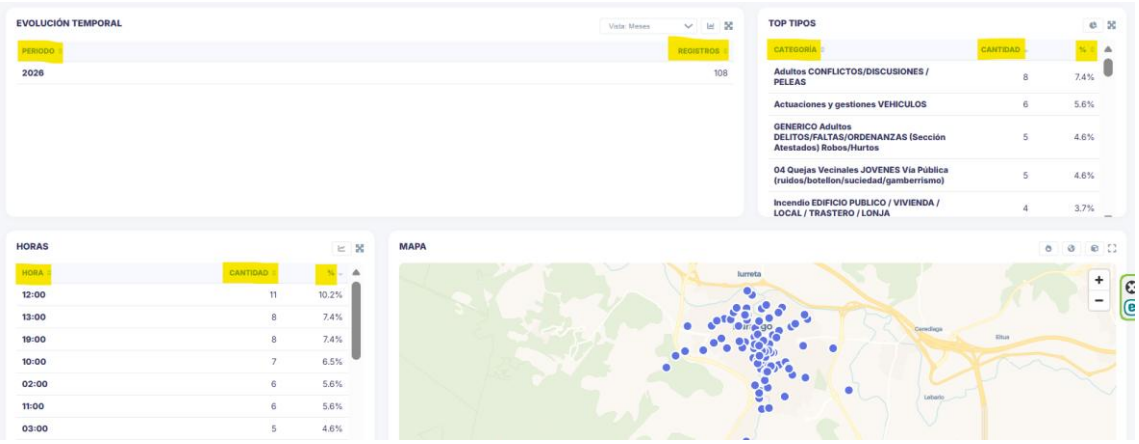
Vista Datos, los cuales se clasifican ascendente/descendente click en parte superior columna